Ситуационный план М 1:2000

План М 1:500

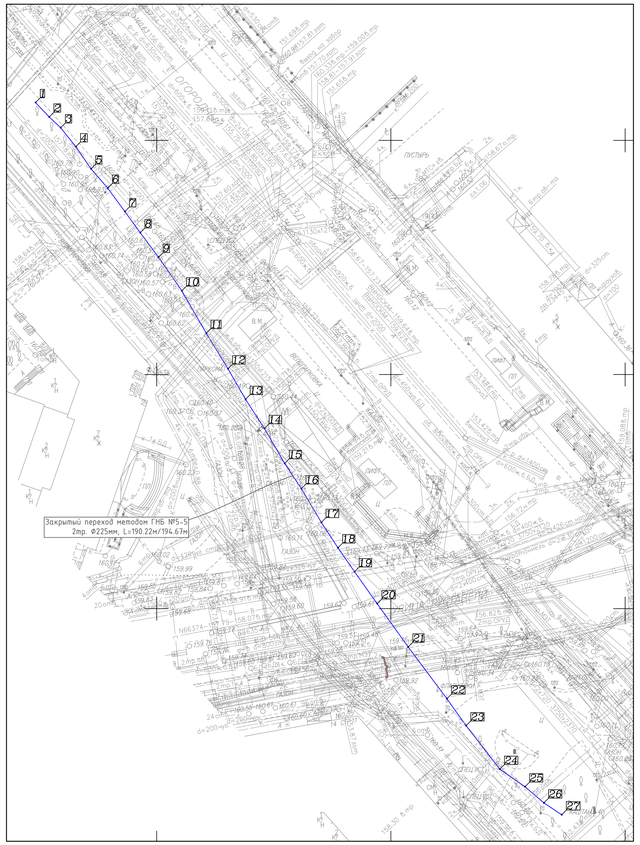

План привязок М 1:500

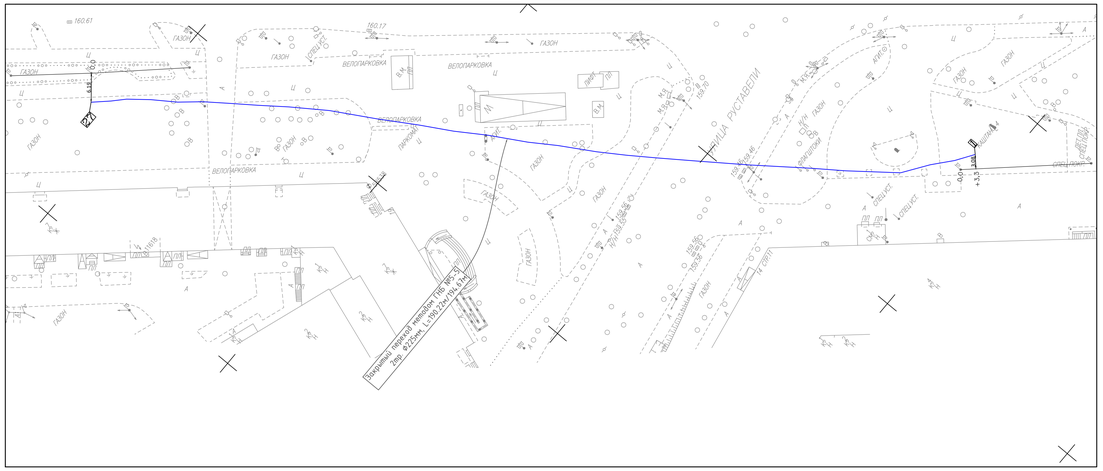

Продольный профиль ГНБ №5-5
Закрытый переход - 190.22м/194.67м

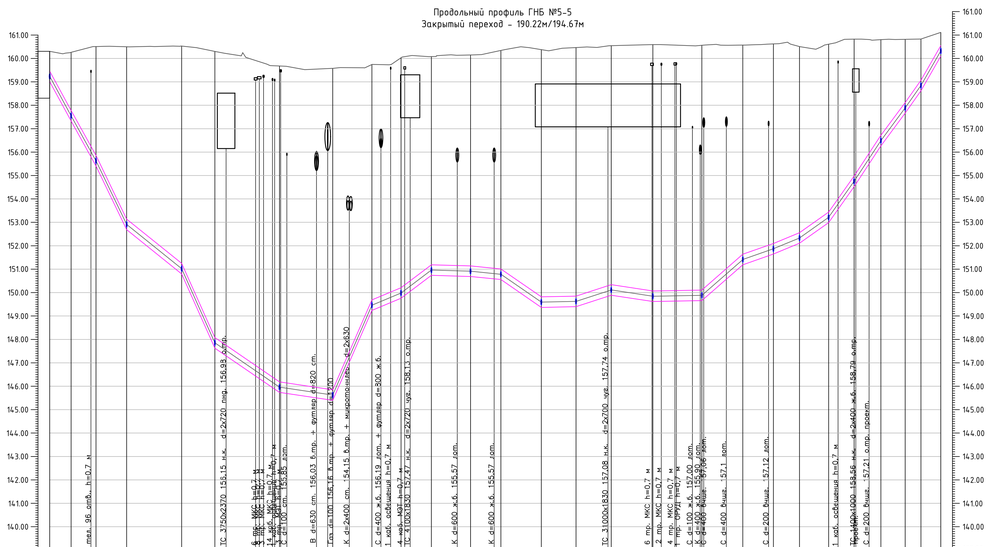

Условные обозначения подземных инженерных коммуникаций

- водопровод (водовод)
- дренаж
- газопровод
- кабель МОСЭНЕРГО
- кабель телевидения
- кабель МПС
- кабель радио
- воздухопровод
- кабель МОСЭЛЕКТРОТРАНС
- бронированный кабель связи
- блочная канализация МОСЭНЕРГО
- кабель заземления
- проекты
- общий коллектор
- водосток
- канализация
- теплопровод
- кабель МОСГОРСВЕТ
- кабель ДС
- кабель связи УПО
- золопровод
- илопровод
- телефон. канализация
- волновод
- каб. колл. МОСЭНЕРГО
- бездейств. прокладки

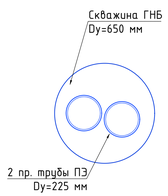

Масштабы:
Горизонтальный 1:500
Вертикальный 1:100

Номера точек	27	26	25	24	23	22	21	20	19	18	17	16	15	14	13	12	11	10	9	8	7	6	5	4	3	2	1
Отметка поверхности земли (м)	160.30	160.28	160.51	160.50	160.53	160.30	159.68	159.58	159.74	160.03	160.08	160.15	160.34	160.38	160.46	160.55	160.59	160.56	160.57	160.62	160.51	160.61	160.82	160.80	160.82	160.83	161.16
Отметка низа трубы (м)	159.12	157.44	155.52	152.80	150.91	147.74	145.85	145.51	149.35	149.87	150.85	150.80	150.67	149.48	149.51	150.00	149.73	149.77	151.30	151.76	152.22	153.10	154.64	156.39	157.79	158.73	160.21
Глубина заложения (м)	0.85	2.59	4.76	7.47	9.39	12.33	13.60	13.84	10.16	9.83	9.00	9.12	9.44	10.67	10.72	10.31	10.63	10.56	9.04	8.63	8.06	7.28	5.95	4.19	2.80	1.87	0.71
Расстояние между точками (м)		4.55	5.31	6.55	11.74	7.09	13.79	11.37	8.36	6.22	6.49	8.35	6.48	8.63	7.40	7.53	8.88	10.47	8.74	6.52	5.58	6.21	5.44	5.73	5.19	3.36	4.24
Длина трубы (м) / Уклон, (м)		1.68 -0.04	1.85 -0.04	2.75 -0.04	4.70 -0.04	3.55 -0.04	5.39 -0.04	5.25 -0.04	4.00 -0.04	3.00 -0.04	3.25 -0.04	4.25 -0.04	3.25 -0.04	4.25 -0.04	3.75 -0.04	3.80 -0.04	4.40 -0.04	5.25 -0.04	4.40 -0.04	3.25 -0.04	2.80 -0.04	3.10 -0.04	2.75 -0.04	2.87 -0.04	2.60 -0.04	1.68 -0.04	2.12 -0.04	
Материал, диаметр труб	Трубы ЭЛЕКТРОПАЙП 225/170-N1250 P2 SDR 13.6, 2шт.																										
Основание	Естественное																										

Съемка выполнена электронным тахеометром Leica TS-06

Система координат МСК

КС 316-26
ТУ №

Lплан = 190.22м
Lпроф = 194.67м

Заказчик	АО «ОЭК»	Подрядчик	ООО «СПЕЦИНЖСТРОЙ»
Исполнительный чертеж закрытого перехода № 5-5. Объект: «Выполнение работ по прокладке КЛ методом горизонтального направленного бурения по объекту: «Резервирование электроснабжения РП 70046» ПО адресу: г. Москва, Огородный проезд, 14стр3			
Проектная организация	ООО «СПЕЦИНЖСТРОЙ»	Проект	04-ОЭКСТ-КС-25-ТКР.1ГЧ
Административная инспекция округа		ТУ №	
Строительство начато	2026	Согласование с ОПС:	
Строительство закончено	2026		
Должность	Подпись	Фамилия	
Гл. инженер		Долодонов В.И.	
Нач. участка		Щеглов Р.А.	
Геодезист		Степанова С.А.	